ONLY FOR THE DEMARCATION AND DEVELOPMENT PURPOSE

Odd site dimensions		
SLNO	Site no	Area (sqm)
1	1	116.90
2	14	131.26
3	15	144.12
4	16	175.22
5	17	98.00
6	30	127.87
7	31	101.03
8	32	79.20
9	33	80.04
10	34	80.88
11	35	81.72
12	36	82.56
13	37	83.40
14	38	84.24
15	39	85.08
16	40	71.39
17	41	111.88
18	44	170.37
19	45	126.02
20	46	104.60
21	47	93.45
22	48	166.22
23	51	158.57
24	52	155.77
25	53	140.77
26	54	140.76
27	55	134.82
28	56	110.36
29	57	92.75
30	58	85.80
31	59	112.76
32	60	124.87
33	61	85.97
34	62	80.61
35	63	67.60
36	64	61.24
37	65	50.76
38	66	438.53
39	67	148.38
40	68	123.74
41	69	122.93
42	70	122.11
43	71	121.30
44	72	120.48
45	73	119.67
46	74	118.85
47	75	118.04
48	76	117.22
49	77	116.41
50	78	115.59
51	79	114.78
52	80	113.97
53	81	133.35
54	82	76.27
55	83	86.05
56	84	86.03
57	85	86.02
58	86	86.00
59	87	85.99
60	88	85.97
61	89	85.96
62	90	85.95
63	91	85.93
64	92	85.92
65	93	85.90
66	94	85.89
67	95	85.87
TOTAL		7,457.96

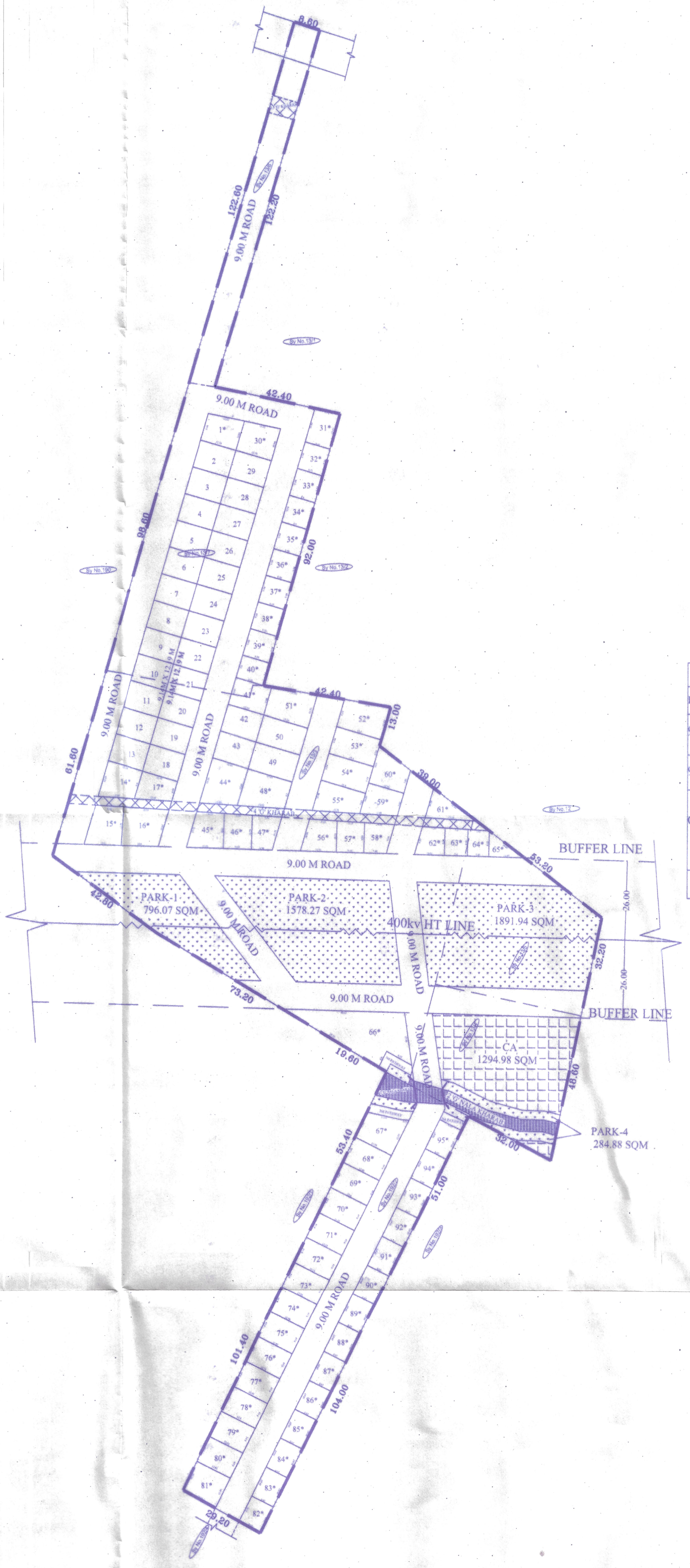
8.60
9.00 M ROAD
122.60
122.20
Sy No.13/1
42.40
9.00 M ROAD
98.60
92.00
Sy No.190
Sy No.13/2
Sy No.13/7
9.14M X 12.19 M
42.40
13.00
61.60
9.00 M ROAD
9.00 M ROAD
39.00
4'0" KHARAB
Sy No.12
BUFFER LINE
53.20
9.00 M ROAD
42.80
PARK-1 796.07 SQM
PARK-2 1578.27 SQM
PARK-3 1891.94 SQM
9.00 M ROAD
400kv HT LINE
9.00 M ROAD
26.00
32.20
73.20
9.00 M ROAD
BUFFER LINE
66*
19.60
CA 1294.98 SQM
48.60
NALA KHARAB
PARK-4 284.88 SQM
32.00
53.40
51.00
9.00 M ROAD
101.40
104.00
29.20
Sy No.192/2

PLOT DETAILS			
DIMENSIONS	SITE NUMBERS	NO. OF SITES	TOTAL AREA IN SQM
9.14M X 12.19M	2,3,4,5,6,7,8,9,10,11,12,13,18,19,20,21,22,23,24,25,26,27,28,29,42,43.	26	2,896.83
9.14M X 15.24M	49,50	02	278.59
ODD SITES*	1,14,15,16,17,30,31,32,33,34,35,36,37,38,39,40,41,44 45,46,47,48,51,52,53,54,55,56,57,58,59,60,61,62,63,64 65,66,67,68,69,70,71,72,73,74,75,76,77,78,79,80,81,82 83,84,85,86,87,88,89,90,91,92,93,94,95.	67	7,457.96
GRAND TOTAL		95	10,633.38

PARK DETAILS	
SL.NO	AREA IN SQM
PARK-1	796.07
PARK-2	1,578.27
PARK-3	1,891.94
PARK-4	284.88
TOTAL	4,551.16

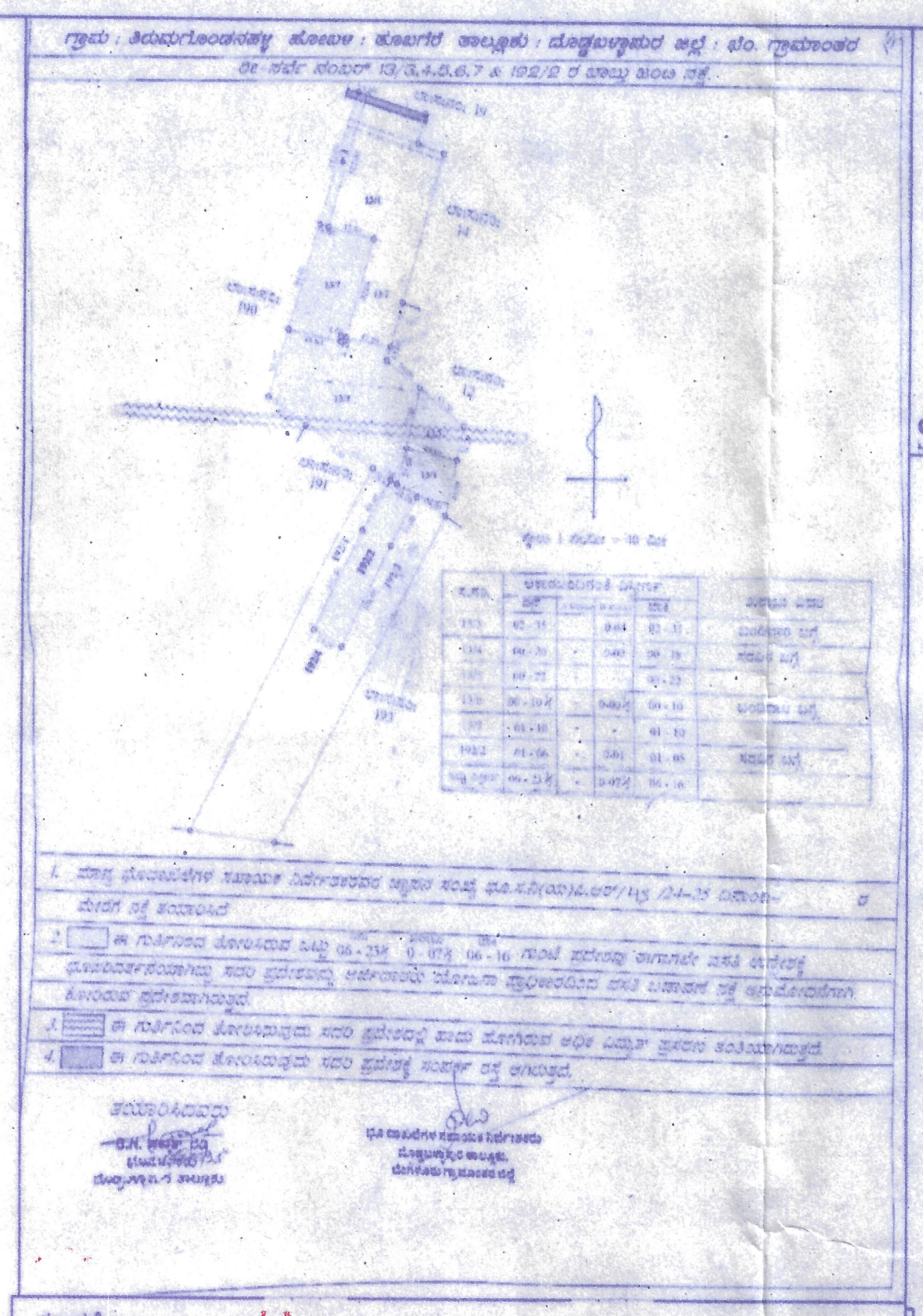
ಗ್ರಾಮ : ತಿರುಮಗೊಂಡನಹಳ್ಳಿ ಹೋಬಳಿ : ತೂಬಗೆರೆ ತಾಲ್ಲೂಕು : ದೊಡ್ಡಬಳ್ಳಾಪುರ ಜಿಲ್ಲೆ : ಬೆಂ. ಗ್ರಾಮಾಂತರ

ಸೂಚನೆ :-

1. ಮೇಲ್ಕಂಡ ಪಟ್ಟಿಯಂತೆ ಮಾನ್ಯ ಜಿಲ್ಲಾಧಿಕಾರಿಗಳು, ಬೆಂಗಳೂರು ಗ್ರಾಮಾಂತರ ಜಿಲ್ಲೆ ರವರಿಂದ ಭೂ ಪರಿವರ್ತನಾ ಆದೇಶವಾಗಿರುತ್ತದೆ.
2. ಭೂ ದಾಖಲೆಗಳ ಸಹಾಯಕ ನಿರ್ದೇಶಕರು, ದೊಡ್ಡಬಳ್ಳಾಪುರ ತಾಲ್ಲೂಕು ಇವರು ದೃಢೀಕರಿಸಿ ಸಲ್ಲಿಸಿರುವ ಸರ್ವೆ ನಕ್ಷೆಯ ಆಧಾರದ ಮೇಲೆ ವಿನ್ಯಾಸ ನಕ್ಷೆಯನ್ನು ತಯಾರಿಸಿದೆ. ಸರ್ವೆ ನಕ್ಷೆಯಲ್ಲಿನ ನ್ಯೂನ್ಯತೆಗಳಿಗೆ ಈ ಪ್ರಾಧಿಕಾರದ ಜವಾಬ್ದಾರಿ ಇರುವುದಿಲ್ಲ.
3. ಈ ಜಮೀನಿನ ಯಾವುದೇ ತಂಟೆ ತಕರಾರುಗಳಿಗೆ ಅರ್ಜಿದಾರರೇ ಹೊಣೆಗಾರರಾಗಿದ್ದು, ಈ ಪ್ರಾಧಿಕಾರಕ್ಕೆ ಯಾವುದೇ ರೀತಿಯ ಜವಾಬ್ದಾರಿ ಇರುವುದಿಲ್ಲ.
4. ದಾಖಲೆಗಳಂತೆ ಪ್ರಶ್ನಿತ ಜಮೀನಿನಲ್ಲಿ 00-01ಗುಂಟೆ 'ಬ' ಖರಾಬು ಪ್ರದೇಶವಿದ್ದು, ಹಾಲಿ ಸ್ಥಳದಲ್ಲಿ ಹಾಗೂ ಟೋಟಲ್ ಸ್ಟೇಷನ್ ನಕ್ಷೆಯಂತೆ ಸುಮಾರು 885.70 ಚ.ಮೀ. ವಿಸ್ತೀರ್ಣದಲ್ಲಿ ನಾಲ ಪ್ರದೇಶವಿದ್ದು, ವಿನ್ಯಾಸ ನಕ್ಷೆಯಲ್ಲಿ ಯಥಾವತ್ತಾಗಿ ಅಳವಡಿಸಲಾಗಿದೆ.

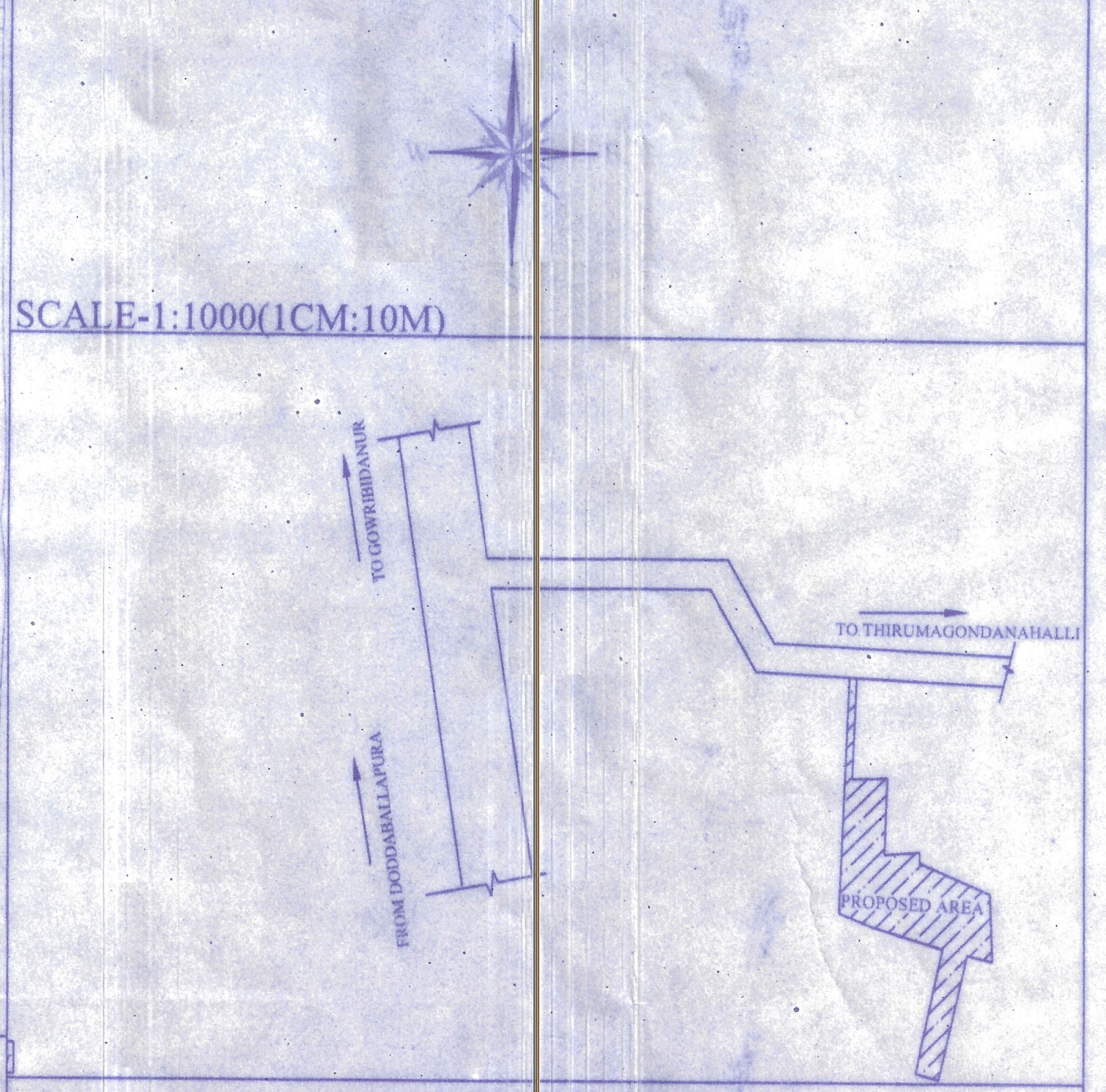
SCALE-1:1000(1CM:10M)
TO GOWRIBIDANUR
FROM DODDABALLAPURA
TO THIRUMAGONDANAHALLI
PROPOSED AREA

LEGENDS

LAYOUT BOUNDARY	▬ ▬
REVENUE SY NO BOUNDARY	— — —
PARK	⠿
CA	▦
CART KHARAB	▩
NALA KHARAB	▇

AREA STATEMENT

SL.NO	VILLAGE NAME	SY.NO	TOTAL EXTENT		A Kharab Guntas	B Kharab Guntas	CONVERSION ORDER No and DATE
			Acres	Guntas			
1	THIRUMAGONDANAHALLI	13/3	02	35	00	04	NO:-697532 Dtd:25-09-2024
2		13/4	00	20	00	02	NO:-697535 Dtd:25-09-2024
3		13/5	00	22	00	00	NO:-697537 Dtd:25-09-2024
4		13/6	00	10.5	00	0.5	NO:-500183 Dtd:17-06-2023
5		13/7	01	10	00	00	NO:-500184 Dtd:17-06-2023
6		192/2	01	06	00	01	NO:-697539 Dtd:25-09-2024
TOTAL			06	23.5	00	7.50	

LAND USE ANALYSIS

TOTAL AREA OF LAYOUT -06ACRES 16 GUNTAS (25,899.52 Sq.m)

SL.NO	DESCRIPTION	AREA IN SQMT	%
1	RESIDENTIAL	10,633.38	41.06 %
2	PARKS	4,551.16	17.57 %
3	CA	1,294.98	5.00 %
4	ROADS	9,420.00	36.37 %
TOTAL AREA		25,899.52	100.00 %

SANCTIONING AUTHORITY

ದಿನಾಂಕ : 24-02-2025 ರಂದು ನಡೆದ 34 ನೇ ಸಭೆಯ ನಡವಳಿಕೆ ಸಂಖ್ಯೆ: 34 38 ರ ಮೇರೆಗೆ ಕರ್ನಾಟಕ ನಗರ ಮತ್ತು ಗ್ರಾಮಾಂತರ ಯೋಜನಾ ಕಾಯ್ದೆ 1961ರ ಕಲಂ 17(2A)ರ ಅಡಿಯಲ್ಲಿ ಪತ್ರ ಸಂಖ್ಯೆ: DPA/TP/LAO/ 17 / 2024-25 ದಿನಾಂಕ: 29-03-2025 ರಲ್ಲಿನ ಷರತ್ತುಗಳಿಗೆ ಒಳಪಟ್ಟು ವಸತಿ/ವಸತಿಯೇತರ ವಿನ್ಯಾಸ ನಕ್ಷೆಗೆ ತಾತ್ಕಾಲಿಕ ಅನುಮೋದನೆ ನೀಡಲಾಗಿದೆ.

29.3.25
ಸದಸ್ಯ ಕಾರ್ಯದರ್ಶಿಗಳು
ದೊಡ್ಡಬಳ್ಳಾಪುರ ಯೋಜನಾ ಪ್ರಾಧಿಕಾರ

29.3.25
ನಗರ ಯೋಜಕರು
ದೊಡ್ಡಬಳ್ಳಾಪುರ ಯೋಜನಾ ಪ್ರಾಧಿಕಾರ.
ದೊಡ್ಡಬಳ್ಳಾಪುರ.

29/3/25
ನಗರ ಮತ್ತು ಗ್ರಾಮಾಂತರ ಯೋಜನಾ ಸಹಾಯಕ ನಿರ್ದೇಶಕರು
ದೊಡ್ಡಬಳ್ಳಾಪುರ ಯೋಜನಾ ಪ್ರಾಧಿಕಾರ
ದೊಡ್ಡಬಳ್ಳಾಪುರ.

OWNERS

M/S SAMRUDH
Rep. by its partner

Theertha

Mr. LAKSHMISHA K J

ENGINEER:

Tejavardhan V
DBP/BL/10067/25-26
Sri Ram Constructions
1st Floor, B Ramegowda Complex
Behind Nagarasabhe, Doddaballapura
Mob: 8951944663

TITLE

DRAFT RESIDENTIAL LAYOUT PLAN IN
SY.Nos. 13/3,13/4,13/5,13/6,13/7,192/2
OF THIRUMAGONDANAHALLI VILLAGE,
TUBAGERE HOBLI, DODDABALAPURA TALUK,